ANTEPROYECTO CONDOMINIO CONSTRUIDO POR ETAPAS

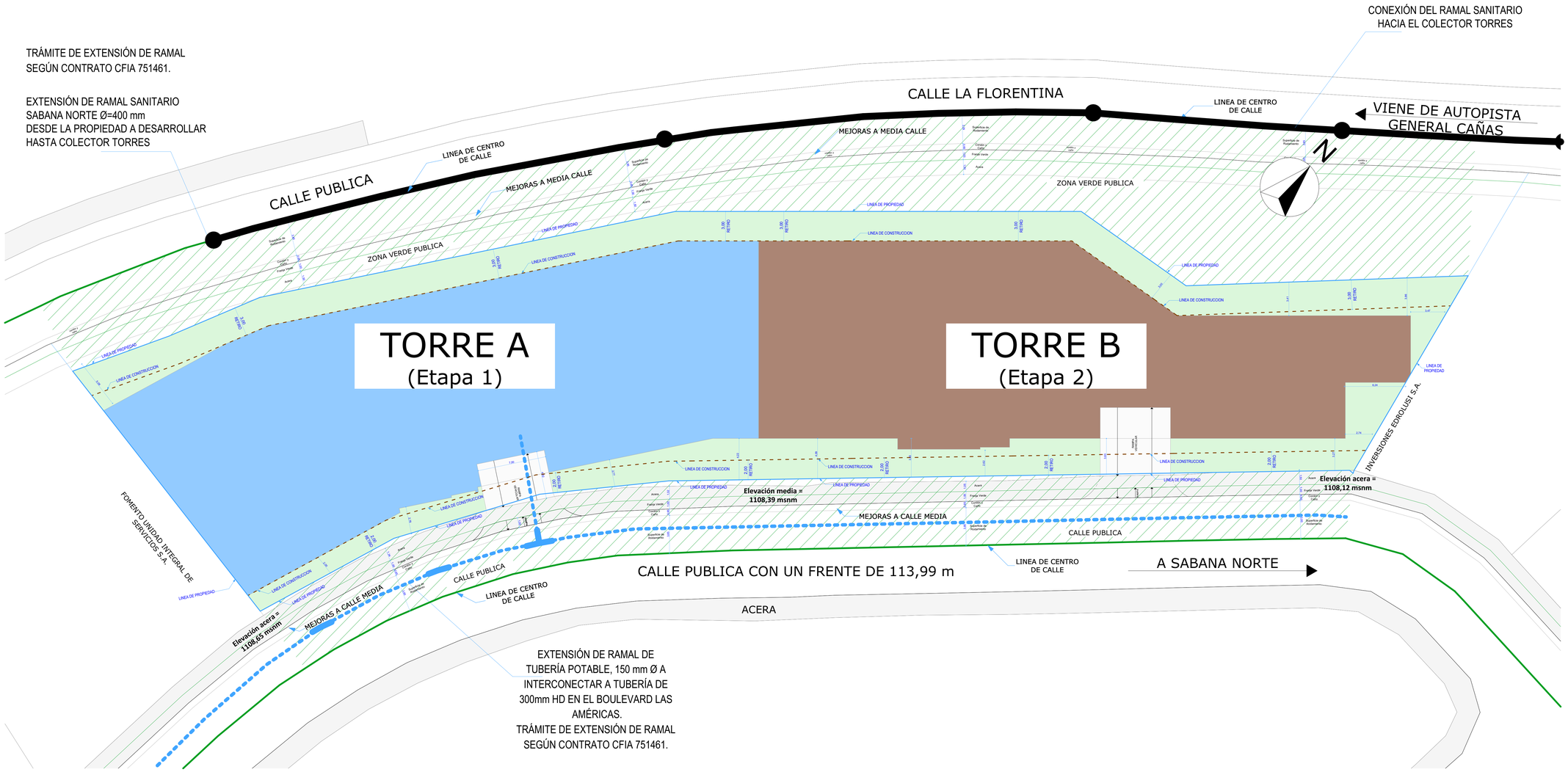

Diseño de Sitio 1:175

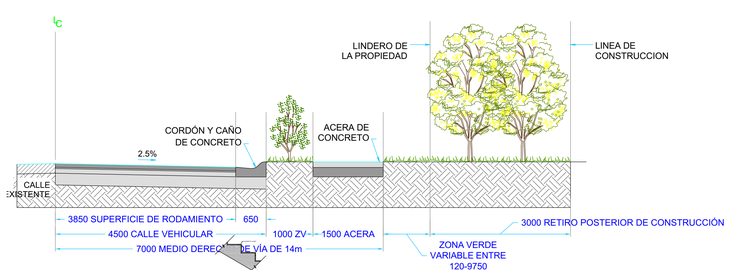

SECCIÓN DE MEJORAS A MEDIA VÍA EN CALLE POSTERIOR

1:50

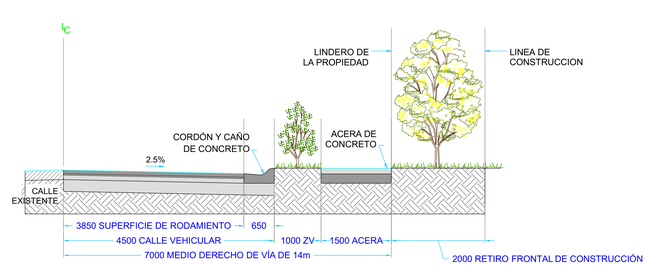

SECCIÓN DE MEJORAS A MEDIA VÍA EN CALLE FRONTAL

1:50

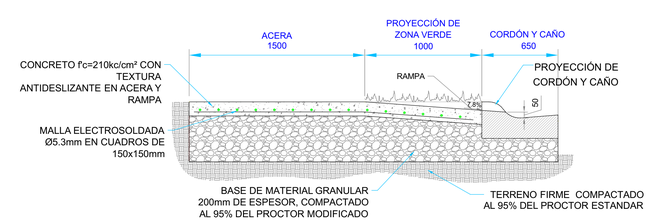

DETALLE DE RAMPA PARA ACCESO VEHICULAR

1:20

EL CONTENIDO DE ESTOS PLANOS CONSTRUCTIVOS ES PROPIEDAD INTELECTUAL DE LA FIRMA GESTION Y CONSULTORIA INTEGRADA GCI S.A., SU REPRODUCCION TOTAL O PARCIAL POR CUALQUIER MEDIO SE ENCUENTRA PROTEGIDA POR EL ARTICULO No.II DEL REGLAMENTO PARA LA CONTRATACION DE SERVICIOS DE CONSULTORIA DEL COLEGIO FEDERADO DE INGENIEROS Y ARQUITECTOS DE COSTA RICA, Y LAS LEYES NACIONALES E INTERNACIONALES QUE REGULAN LA MATERIA. ES NECESARIO POR LO TANTO LA AUTORIZACION PREVIA PARA HACER USO DE CUALQUIERA DE SUS PARTES.

REV.	DESCRIPCIÓN	APROBÓ	FECHA	DIBUJÓ
-	-	-	-	-
-	-	-	-	-
-	-	-	-	-
-	-	-	-	-

PROYECTO:

CONDOMINIO VERTICAL RESIDENCIAL SABANA 60

GESTIÓN Y CONSULTORÍA INTEGRADA GCI S.A.
Tel: (506) 2290-8675
Fax: (506) 2220-3547
E-mail: gci@gcicrg.com
GCI INGENIERIA

Colegio Federado de Ingenieros y de Arquitectos de Costa Rica

CONTRATO	OC 933114
MONTO	¢ 236,936,000.00
FECHA VISADO CFIA	15/07/2020
CATASTRO	SJ-1328152-2009
TAMAÑO	45,436 M2
REGISTRADO POR	04794
BITACORA	

ESTE SELLO TIENE UNA VIGENCIA DE UN AÑO. VENCE EL 15/07/2021 (vencimiento aplica sólo a planos constructivos)

SI NO HAY CONCORDANCIA ENTRE LA INFORMACIÓN DEL SELLO Y EL RESULTADO DE LA CONSULTA MEDIANTE EL CÓDIGO, EL SELLO ES NULO.

NOMBRE DEL PROYECTO	
Modificación #2 Anteproyecto Condominio Vertical Residencial Sabana 60	
CLASIFICACIÓN SEGÚN DECRETO 36550	
MODIFICACIÓN ANTEPROYECTO	
PROPIETARIO	**CÉDULA**
3-101-730036	3-101-730036
DIRECCIÓN	**UBICACIÓN**
SABANA NORTE, 400M OESTE Y 400M NORTE DEL ICE	PROVINCIA: SAN JOSÉ CANTÓN: SAN JOSÉ DISTRITO: MATA REDONDA
SERVICIOS DE OPERACIÓN , MANTENIMIENTO Y OTRAS CONSULTORÍAS	
CONSULTORÍA VARIAS	A-20133 CHAVERRI CERDAS ERIKA A-17012 RODRIGUEZ ROMERO MICHAEL

Proyecto aprobado por Luis Diego Jiménez López de Acueductos y Alcantarillados, Erika María Lutz Cruz de Instituto Nacional de Vivienda y Urbanismo, Esteban Zumbado Acevedo del Ministerio de Salud

Cuenta con Rectificación de Áreas

MODIFICACIÓN #2

ESTA LAMINA SUSTITUYE A LA LÁMINA A-1000.1 APROBADA POR LA DIRECCIÓN DE URBANISMO EN JUL-2018 OC 828557, BAJO EL NÚMERO DE PLANO SJ-1328152-2009

Se actualiza Huella del Edificio por modificación de TORRE B

INFORMACIÓN DEL REGISTRO PUBLICO:

PROPIETARIO: 3-101-730036 SOCIEDAD ANONIMA
N° CATASTRO: SJ-1328152-2009
CITAS: TOMO: FOLIO:
FOLIO REAL: 1-607531-000

CONTENIDO
Diseño de Sitio

FECHA DE IMPRESIÓN: 21/08/2020

PROYECTO No.	FECHA	CÓDIGO
503	AGOSTO/2020	A-1000.1
LÁMINA No.	LÁMINAS TOTALES	
A-1000.1	152	